Similar Weather Chart Analysis Report

[Query Image] surf_anlmod_pa4_2025031406.gif

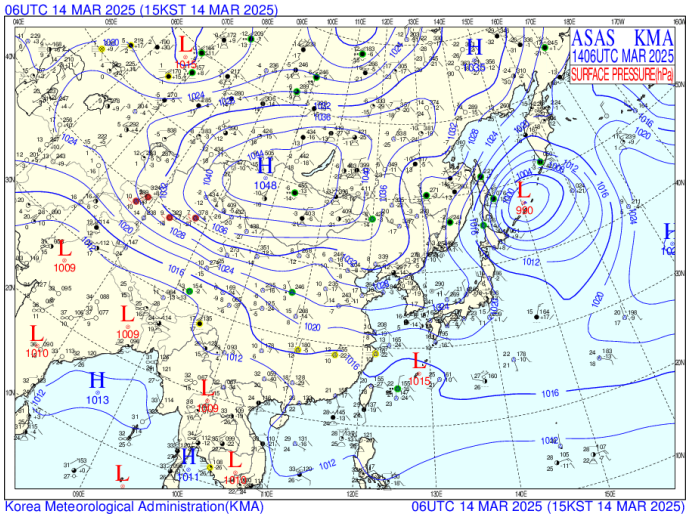

[Top 1] surf_anlmod_pa4_2023112706.gif (Similarity: 15.0%)

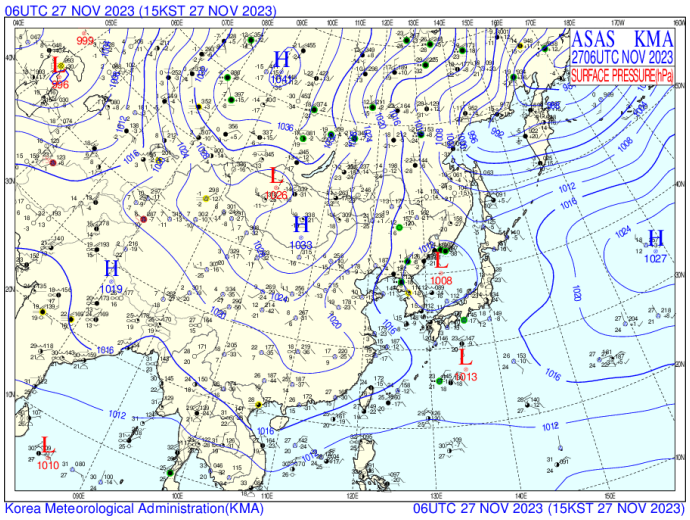

[Top 2] surf_anlmod_pa4_2023032806.gif (Similarity: 0.0%)

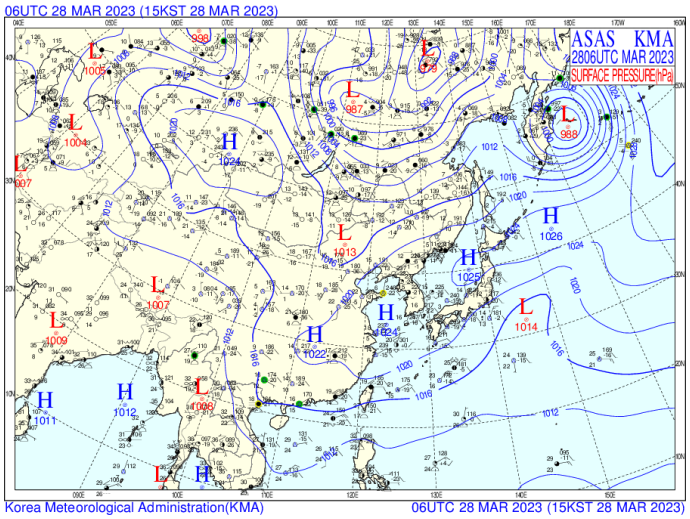

Similar Weather Chart Analysis Report

[Top 3] surf_anlmod_pa4_2023032806.gif (Similarity: 0.0%)

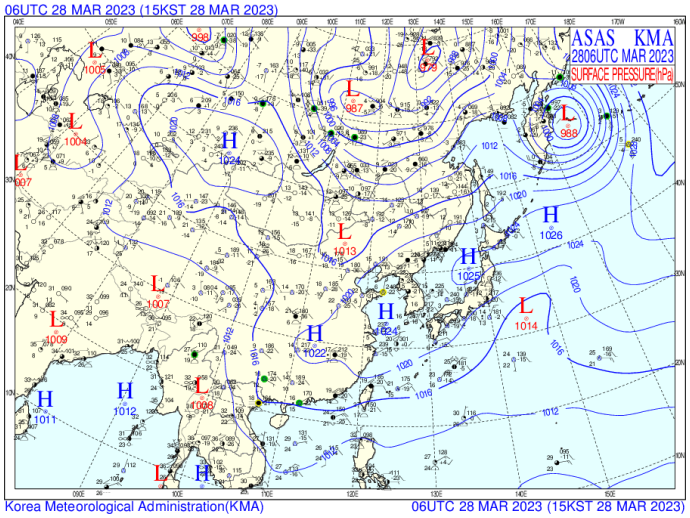

GPT Analysis:

대기 현상 분석 보고서

1. [질의 이미지 (2025년 3월 14일)]의 핵심 날씨 특징 요약

질의 이미지는 2025년 3월 14일 15시 KST(UTC+9)에 작성된 한국 기상청(ASAS KMA)의 표면 기압도입니다. 이 날씨 상황은 동아시아 지역에서 매우 활발한 저기압 시스템과 고기압 시스템의 상호작용으로 특징지어집니다.

* **주요 저기압 시스템 (L):** 일본 열도 북동부 해상에 중심기압 980hPa의 강력한 저기압이 위치하며, 이는 강한 동북풍을 동반하여 일본 및 동해 지역에 강풍과 비를 유발할 가능성이 높습니다. 또한, 중국 동부 해안과 동아시아 대륙 북부 해안에도 여러 개의 저기압(예: 1009hPa, 1007hPa)이 존재하며, 이들 시스템은 북서풍과 함께 북쪽으로 이동하는 추세를 보입니다.
* **주요 고기압 시스템 (H):** 중국 중부 및 동부 해안, 그리고 일본 열도 북서부 해상에 중심기압 1048hPa, 1035hPa, 1027hPa의 고기압이 존재합니다. 이 고기압은 상대적으로 안정적인 날씨를 유지하며, 특히 중국 중부와 동해 지역에서는 북서풍이 강하게 발달하여 기온이 상승할 수 있습니다.

Similar Weather Chart Analysis Report

* **기압 등위선 분포:** 기압 등위선이 매우 밀집되어 있어, 특히 저기압 중심 부근에서 강한 기압 경사가 존재함을 알 수 있습니다. 이는 강한 풍속을 의미하며, 날씨의 불안정성을 높입니다.
* **기온 분포:** 대륙 내부는 10~15의 낮은 기온을 보이며, 해안 및 해상 지역은 15~25의 높은 기온을 보입니다. 이는 대륙과 해양 사이의 열역학적 차이에 기인합니다.
* **전체적인 날씨 상황:** 이 날씨 상황은 동아시아 지역에서 강한 기압 불균형과 풍속 변화를 특징으로 하며, 특히 일본 및 동해 지역에서는 강풍과 비, 그리고 기온의 급격한 변화가 예상됩니다.

2. [상위 3개 유사 날씨도]의 주요 특징, 유사성 및 차이점

순위	날짜	주요 특징	유사성 및 차이점	유사도 (%)
상위 1	2023년 3월 28일	동아시아 지역에서 강력한 저기압(988hPa)이 일본 열도 북동부 해상에 위치하며, 동해 지역에 강한 동북풍을 유발합니다. 또한, 중국 중부 및 동부 해안에 고기압(1026hPa, 1024hPa)이 존재하며, 이는 상대적으로 안정적인 날씨를 유지합니다.	**유사성:** 저기압 위치(일본 열도 북동부), 고기압 위치(중국 중부 및 동부 해안), 기압 등위선 밀도, 기온 분포(대륙 내부 낮음, 해안 높음)가 유사합니다. **차이점:** 질의 이미지(2025년 3월 14일)에서는 저기압 중심기압이 980hPa이며, 고기압 중심기압이 1048hPa, 1035hPa로 더 높습니다. 또한, 2023년 3월 28일 이미지에서는 중국 중부에 있는 고기압이 더 강력한 것으로 보입니다.	**15.0%**
상위 2	2023년 11월 27일	동아시아 지역에서 저기압(996hPa)이 일본 열도 북동부 해상에 위치하며, 동해 지역에 강한 동북풍을 유발합니다. 또한, 중국 중부 및 동부 해안에 고기압(1033hPa, 1027hPa)이 존재하며, 이는 상대적으로 안정적인 날씨를 유지합니다.	**유사성:** 저기압 위치(일본 열도 북동부), 고기압 위치(중국 중부 및 동부 해안), 기압 등위선 밀도, 기온 분포(대륙 내부 낮음, 해안 높음)가 유사합니다. **차이점:** 질의 이미지(2025년 3월 14일)에서는 저기압 중심기압이 980hPa이며, 고기압 중심기압이 1048hPa, 1035hPa로 더 높습니다. 또한, 2023년 11월 27일

Similar Weather Chart Analysis Report

이미지에서는 중국 중부에 있는 고기압이 더 강력한 것으로 보입니다. | **0.0%** |

| **상위 3** | 2023년 3월 28일 | 동아시아 지역에서 강력한 저기압(988hPa)이 일본 열도 북동부 해상에 위치하며, 동해 지역에 강한 동북풍을 유발합니다. 또한, 중국 중부 및 동부 해안에 고기압(1026hPa, 1024hPa)이 존재하며, 이는 상대적으로 안정적인 날씨를 유지합니다. | **유사성:** 저기압 위치(일본 열도 북동부), 고기압 위치(중국 중부 및 동부 해안), 기압 등위선 밀도, 기온 분포(대륙 내부 낮음, 해안 높음)가 유사합니다. **차이점:** 질의 이미지(2025년 3월 14일)에서는 저기압 중심기압이 980hPa