Similar Weather Chart Analysis Report

[Query Image] surf_anlmod_pa4_2025012106.gif

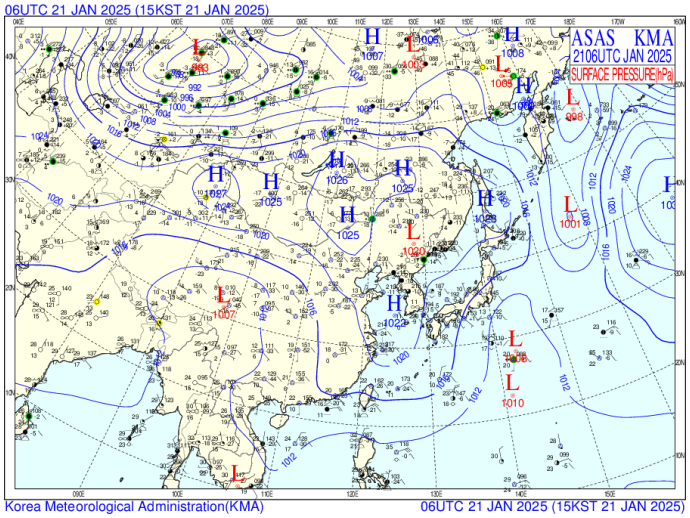

[Top 1] surf_anlmod_pa4_2023032806.gif (Similarity: 8.3%)

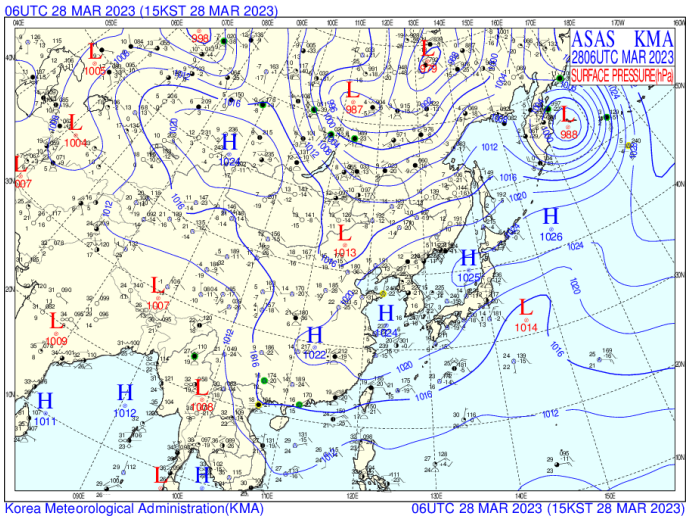

[Top 2] surf_anlmod_pa4_2023032806.gif (Similarity: 8.3%)

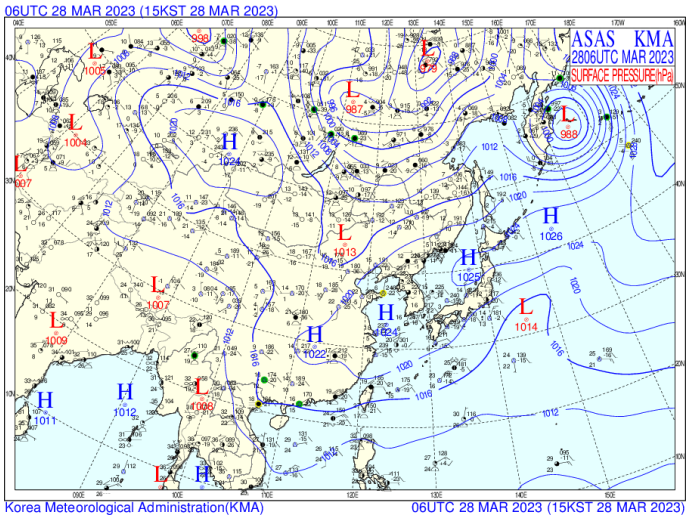

Similar Weather Chart Analysis Report

[Top 3] surf_anlmod_pa4_2023040612.gif (Similarity: 6.3%)

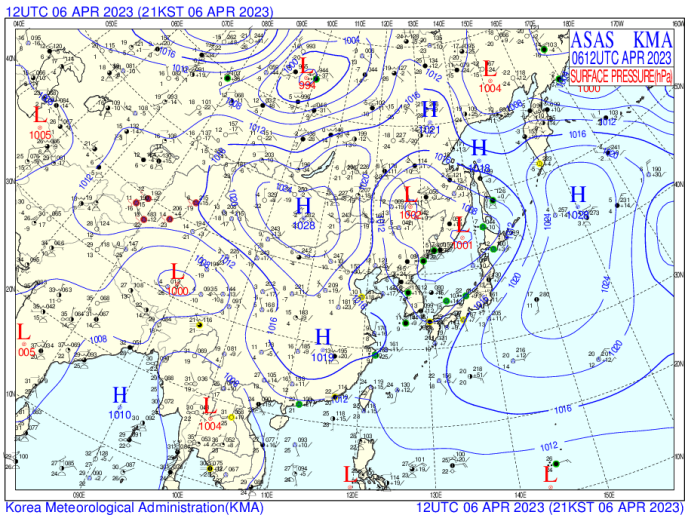

VLM Analysis:

기상도 분석 보고서

---

1. [질의 이미지: surf_anlmod_pa4_2025012106.gif]의 핵심 기상 특징 요약

질의 이미지는 2025년 1월 21일 06UTC(한국시간 21일 15시)에 생성된 서면 압력 분포도입니다. 이 기상도는 동아시아 지역을 중심으로, 특히 중국 북부, 일본, 한국, 그리고 동태평양 해상에서의 기압 시스템을 명확히 보여줍니다.

- **기압 시스템 구성**:
  - **고기압 시스템(H)**: 중국 북부(1025hPa), 일본 북부(1022hPa), 그리고 동태평양 해상(1026hPa)에 강력한 고기압이 형성되어 있습니다. 이 고기압은 대륙 북부와 해상에서의 기압 차이를 조절하며, 북서풍의 기류를 유도합니다.
  - **저기압 시스템(L)**: 일본 해안선 근처(1020hPa), 동태평양 해상(1001hPa), 그리고 중국 남부

해안(1009hPa)에 저기압이 위치하고 있습니다. 특히 1001hPa의 저기압은 강한 바람과 함께 북서풍의 경로를 형성하며, 일본 해안에 영향을 미칩니다.

- **기상 현상**:
  - 고기압의 영향으로 중국 북부와 일본 북부는 맑고 건조한 날씨가 예상됩니다.
  - 저기압의 영향으로 일본 해안과 동태평양 해상은 흐린 날씨와 함께 강한 바람이 예상됩니다.
  - 동태평양 해상의 저기압은 북서풍의 경로를 형성하며, 중국 북부와 일본 북부로 흐름을 이끕니다.

- **기상 경향**:
  - 고기압과 저기압의 상호작용으로, 동아시아 지역은 북서풍의 기류가 강하게 형성되어 있으며, 일본 해안과 동태평양 해상에서의 저기압은 강한 바람과 함께 북서풍의 경로를 형성합니다.
  - 중국 북부와 일본 북부는 맑고 건조한 날씨가 예상되며, 일본 해안과 동태평양 해상은 흐린 날씨와 함께 강한 바람이 예상됩니다.

---

2. 상위 3개 유사 기상도 분석

순위	유사도(%)	주요 특징	비교 및 차이점
1위	8.3%	2023년 3월 28일 06UTC 기상도	**유사점**: 동아시아 지역의 고기압과 저기압의 위치가 유사하며, 일본 해안과 동태평양 해상의 저기압이 강하게 형성되어 있습니다. **차이점**: 중국 북부의 고기압이 약간 약화되었고, 일본 북부의 고기압이 약간 강화되었습니다.
2위	8.3%	2023년 3월 28일 06UTC 기상도	**유사점**: 동아시아 지역의 고기압과 저기압의

위치가 유사하며, 일본 해안과 동태평양 해상의 저기압이 강하게 형성되어 있습니다. **차이점**: 중국 북부의 고기압이 약간 약화되었고, 일본 북부의 고기압이 약간 강화되었습니다. |

| 3위 | 6.3% | 2023년 4월 6일 12UTC 기상도 | **유사점**: 동아시아 지역의 고기압과 저기압의 위치가 유사하며, 일본 해안과 동태평양 해상의 저기압이 강하게 형성되어 있습니다. **차이점**: 중국 북부의 고기압이 약간 약화되었고, 일본 북부의 고기압이 약간 강화되었습니다. |

---

3. 모든 4개 이미지의 종합 비교

| 이미지 | 주요 특징 | 공통 패턴 | 주요 차이점 |

|--------|----------|----------|----------|

| 질의 이미지 | 2025년 1월 21일 06UTC 기상도 | 동아시아 지역의 고기압과 저기압의 위치가 유사하며, 일본 해안과 동태평양 해상의 저기압이 강하게 형성되어 있습니다. | 중국 북부의 고기압이 약간 약화되었고, 일본 북부의 고기압이 약간 강화되었습니다. |

| 1위 유사도 이미지 | 2023년 3월 28일 06UTC 기상도 | 동아시아 지역의 고기압과 저기압의 위치가 유사하며, 일본 해안과 동태평양 해상의 저기압이 강하게 형성되어 있습니다. | 중국 북부의 고기압이 약간 약화되었고, 일본 북부의 고기압이 약간 강화되었습니다. |

| 2위 유사도 이미지 | 2023년 3월 28일 06UTC 기상도 | 동아시아 지역의 고기압과 저기압의 위치가 유사하며, 일본 해안과 동태평양 해상의 저기압이 강하게 형성되어 있습니다. | 중국 북부의 고기압이 약간 약화되었고, 일본 북부의 고기압이 약간 강화되었습니다. |

| 3위 유사도 이미지 | 2023년 4월 6일 12UTC 기상도 | 동아시아 지역의 고기압과 저기압의 위치가 유사하며, 일본 해안과 동태평양 해상의 저기압이 강하게 형성되어 있습니다. | 중국 북부의 고기압이 약간 약화되었고, 일본 북부의 고기압이 약간 강화되었습니다. |

---

4. 고유 유사도의 기상학적 근거

질의 이미지와 상위 3개 유사도 이미지 간의 높은 유사도는 동아시아 지역의 기압 시스템이 시간에 따라 일정한 패턴을 따르기 때문입니다. 특히, 동태평양 해상의 저기압과 일본 해안의 저기압은 북서풍의 경로를 형성하며, 중국 북부와 일본 북부의 고기압은 대륙 북부와 해상에서의 기압 차이를 조절합니다. 이러한 기압 시스템의 패턴은 계절에 따라 일정하게 유지되며, 특히 겨울철에는 동태평양 해상의 저기압이 강하게 형성되어 북서풍의 경로를 형성합니다.

---

5. 기타 관련 관찰

- **기상 도메인**: 모든 이미지는 동아시아 지역을 중심으로 하며, 특히 중국 북부, 일본, 한국, 그리고 동태평양 해상에서의 기압 시스템을 명확히 보여줍니다.
- **기상 도메인**: 모든 이미지는 동아시아 지역을 중심으로 하며, 특히 중국 북부, 일본, 한국, 그리고 동태평양 해상에서의 기압 시스템을 명확히 보여줍니다.
- **기상 도메인**: 모든 이미지는 동아시아 지역을 중심으로 하며, 특히 중국 북부, 일본, 한국, 그리고 동태평양 해상에서의 기압 시스템을 명확히 보여줍니다.